제주도 전기차 충전소 실시간 현황 확인

오픈소스 개발 방법론

3팀: 부김현이

Contents

01 프로젝트 개요

02 데이터 수집 및 전처리

03 예상 결과 및 대안

01 프로젝트 개요

- **프로젝트 선정 이유**: 전국에서 가장 높은 전기차 보급률을 자랑하는 제주도의 특성에 맞춰, 이용자 중심의 충전 인프라 정보 서비스 구현 목표.
- **프로젝트 웹 기능**: 단순히 위치를 파악하는 것을 넘어, 현재 이용 가능한 충전소의 실시간 현황을 한눈에 확인할 수 있는 웹 환경을 구축 목표.

읍면동별 충전소 개수
분석 및 상위 지역 도출

급속/완속 충전기 여부
필터 기능 구현

충전소의 위치
기반 분포 확인

02 데이터 수집 및 전처리

데이터 출처: 제주 데이터허브 및 공공데이터 포털

02 데이터 수집 및 전처리

chargingPlace (충전소 위치)	chargingPlaceDetail (충전소 위치 상세)	holiday (휴점일)	startTime (이용 가능 시작 시각)	addressDoro (도로명 주소)	latitude (위도)
endTime (이용 가능 종료 시각)	chargingFlag (완속 충전 가능 여부)	quickChargingFlag (급속 충전 가능 여부)	quick_charging_type (급속 충전 타입)	anagementCompany (관리 업체명)	longitude (경도)
chargerCount (완속 충전기 대수)	quickChargerCount (급속 충전기 대수)	parkingFeeFlag (주차료 부과 여부)	addressJibu (지번 주소)	provider (제공 기관명)	baseDate (기준일)

데이터 출처: 제주 데이터허브 및 공공데이터 포털

02 데이터 수집 및 전처리

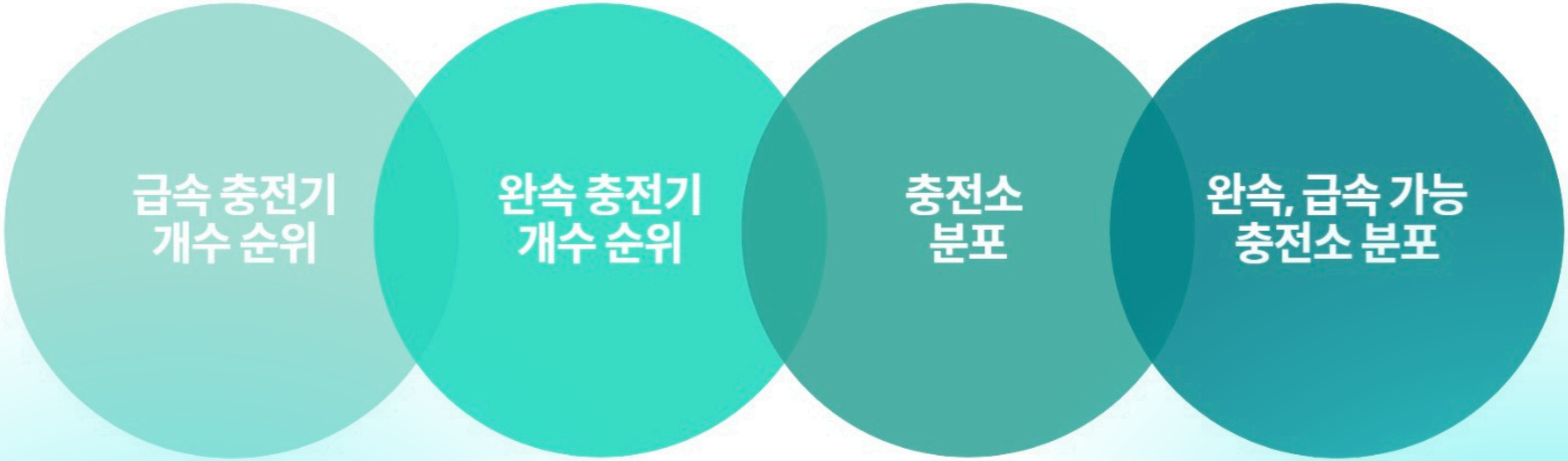

데이터 출처: 제주 데이터허브 및 공공데이터 포털

03 예상 결과 및 대안

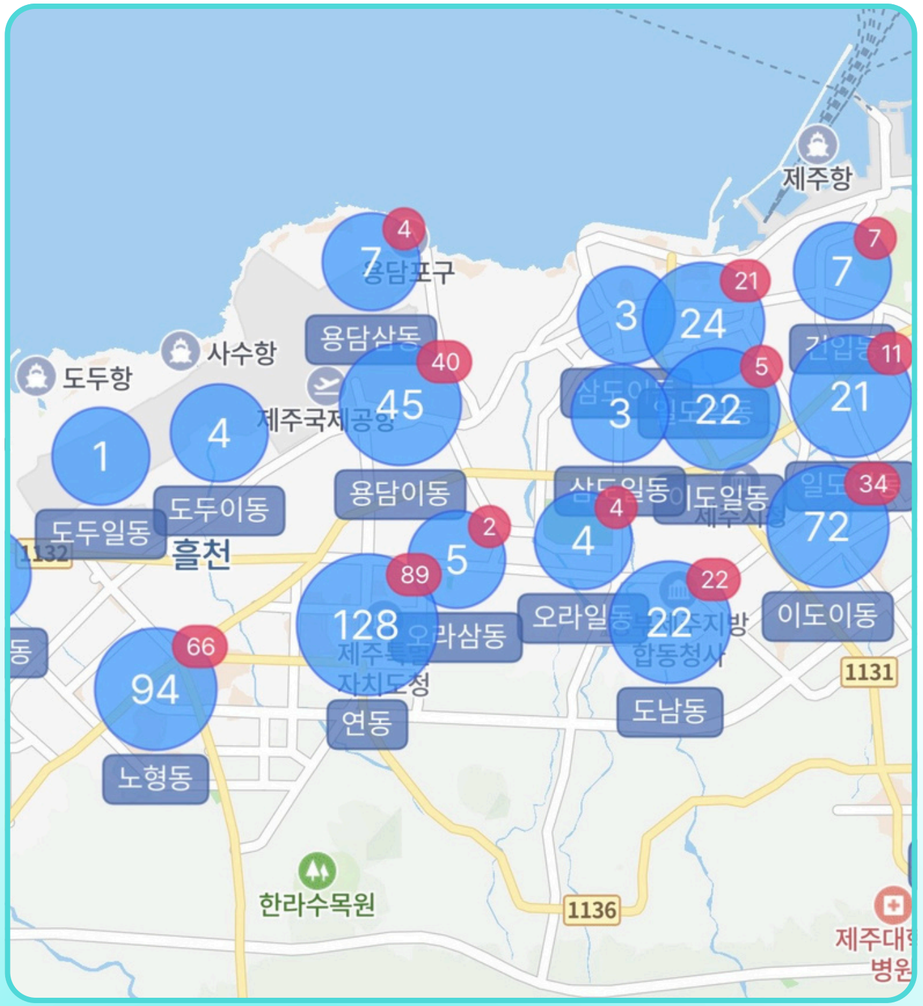
제주항
용담포구
사수항
도두항
용담삼동
제주국제공항
도두이동
도두일동
흘천
용담이동
삼도일동
이도일동
이도이동
오라일동
오라삼동
합동청사
도남동
연동
노형동
한라수목원
1132
1131
1136

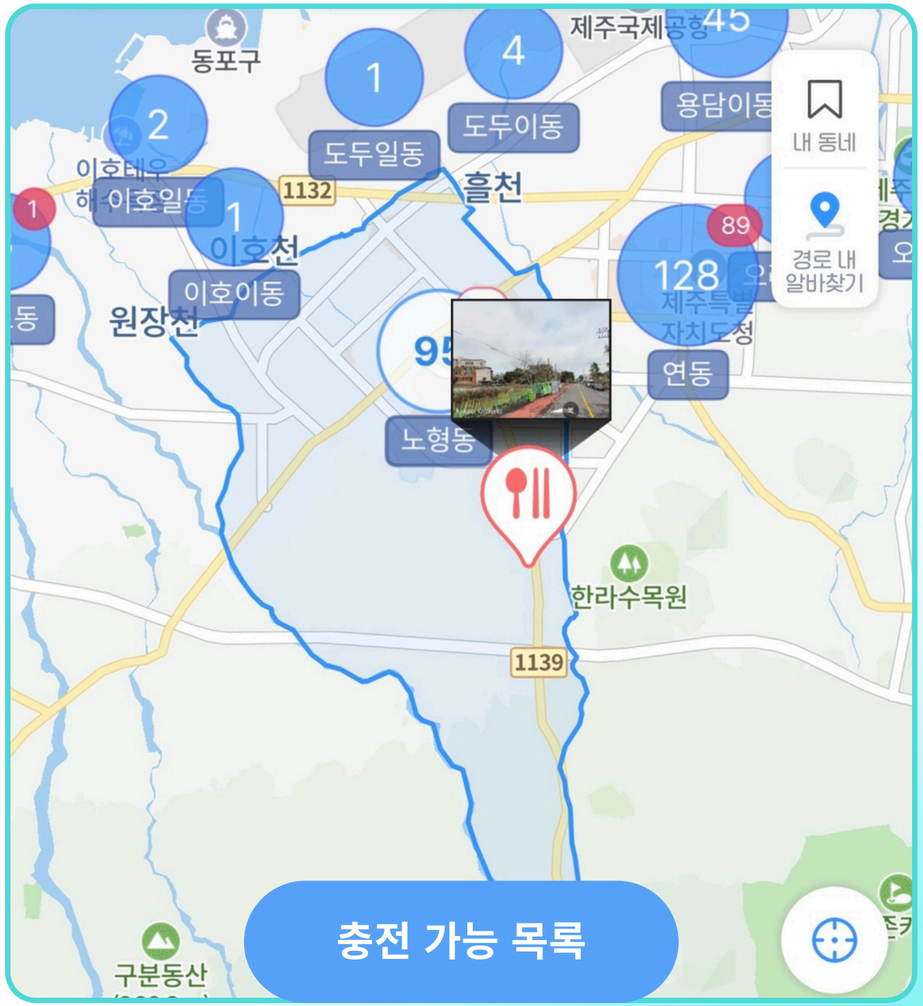
동포구
제주국제공항
도두일동
도두이동
용담이동
흘천
이호일동
이호천
이호이동
원장천
연동
노형동
한라수목원
구분동산
1132
1139
내 동네
경로 내 알바찾기
충전 가능 목록

03 예상 결과 및 대안

- **웹 기능을 구현하지 못할 경우**: 이와 같은 데이터 분석을 진행하여 인사이트를 도출할 예정

충전기 분포

읍면동 별 급속 충전기 개수 순위

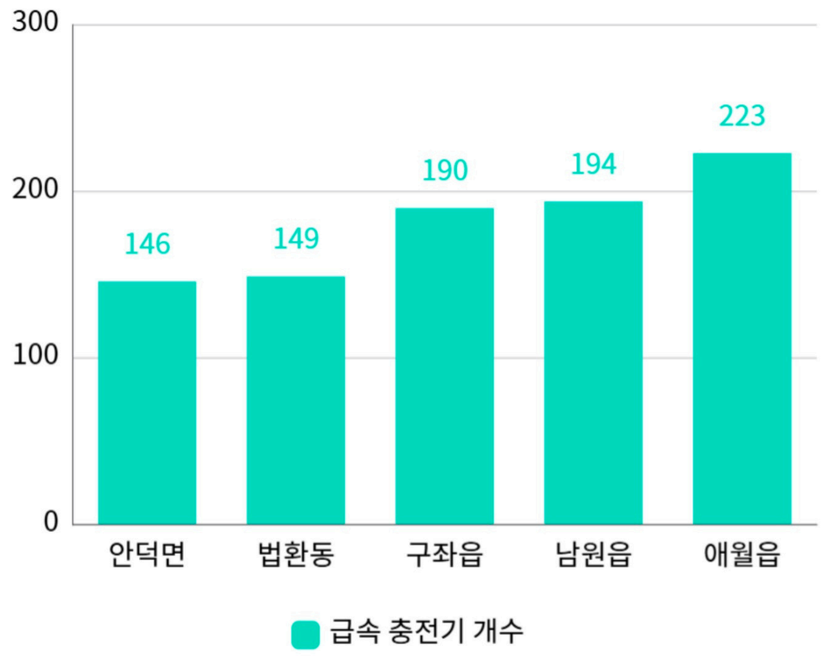

읍면동 별 완속 충전기 개수 순위

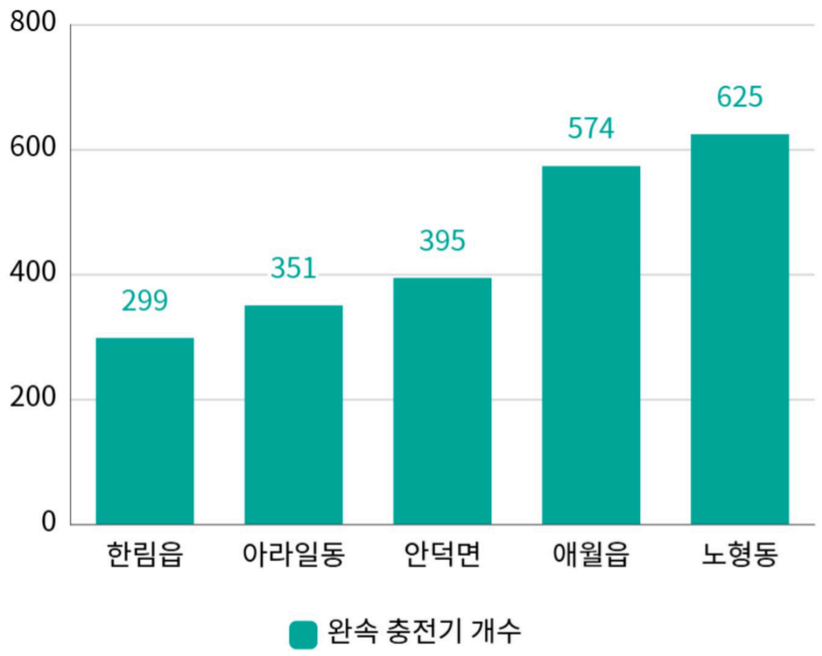

Thank you

발표자: 현재승
2026.04.30